가치 걸음

보행약자 개인맞춤형 길 안내 서비스

최종 PPT

2팀 보행온
임승재 /2021125054
권도윤 /2022125002
차상국 /2023125062
김가은 /2024125006
남보영 /2024125021

04

프로토타이핑 단계 진행 상황

플로우차트 & 와이어프레임 — 01

프로토타입: 미리보기 — 02

계획 대비 효과 자체 평가 — 03

플로우차트

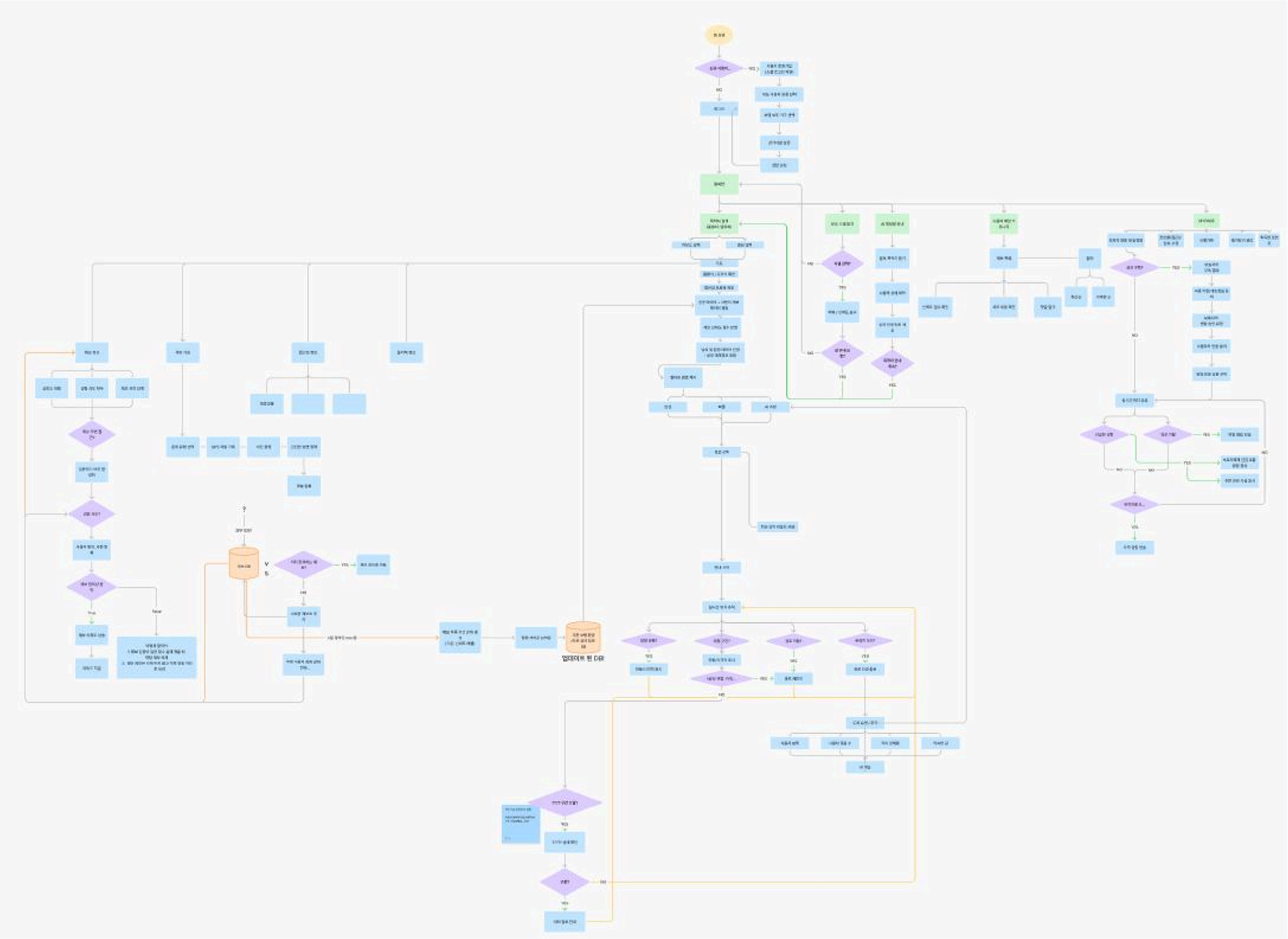

와이어프레임



프로토타입 미리보기: 경로 안내

위험구간 표시

실시간 도움요청/제보

시각장애인용 화면

프로토타입 미리보기: 위험 제보 / 검증

실시간 제보

커뮤니티 검증

원클릭 제보

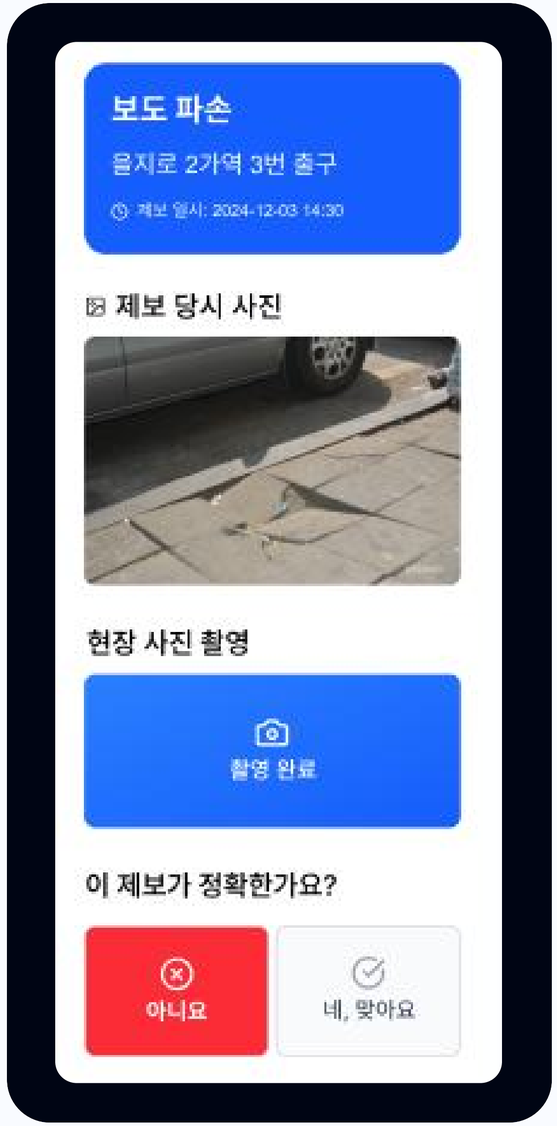

계획대비 효과 자체 평가

대상자
고령자 위주 → 고령자 포함 교통약자로 재정의: 대상자별 요구사항 명확화

수익모델
보호자 대상 프리미엄 구독모델과 B2G 대상으로 구상: 현실성↑

핵심 기능
음성 위주 보행 네비게이션 → 음성, 시각, 진동 모두 활용한 멀티모달 보행 네비게이션
지역기반 커뮤니티 추가→사용자 데이터 제보 활성화
아이디어 구체화→Use Case: 상황별 기능 요구사항 명세

→초기 제안서 요구 사항·타겟의 확대·수정·구체적 명시 효과

계획대비 효과 자체 평가

기대효과

교통약자 : 디지털 접근성↑, 교통약자의 외출, 신체 활동↑, 장애인의 이동권↑

보호자 : 보호자의 안심도↑, 돌봄 스트레스↓

사회적 측면 : 안전한 보행으로 교통사고/구조 등의 비용↓

지자체 : 데이터 기반 취약구간 정비 우선순위, 예산 효율화

Q&A

발표를 들어주셔서 감사합니다.

2팀 보행온